KOENIG Victor

Université Paul Valéry,

Montpellier Département de Géographie

Licence 2 de Géographie

Cartographie et Statistiques TE44GA

Analyse de l'entretien et de la sécurité cyclable de l'agglopôle de Sète

Année universitaire 2024-2025

Sous la responsabilité de Mme LE TEXIER, M. PEROCHE et Mme BANTON

INTRODUCTION GÉNÉRALE.....p. 1

I) Les aménagements cyclables dans l'agglomération de Sète

I.1) Qualité des infrastructures selon les retours des habitants .....……..... p. 3

I.2) Perception des efforts communaux en faveur de vélo .....……..... p. 5

II) La sécurité des cyclistes au quotidien

II.1) Ressenti global en matière de sécurité à vélo .....……...…..... p. 7

II.2) Lecture croisée entre qualité des aménagements et sécurité perçue…..…..... p. 9

III) La fiabilité des données peut-elle être remise en cause par une insuffisance de réponses ?

III.1) Taux de réponse relatif aux habitant très disproportionné

III.2) En inadéquation avec le recensement total des points

CONCLUSION GÉNÉRALE ..... p.

INTRODUCTION

Dans un contexte où l'on cherche à promouvoir un accompagnement dans la transition écologique, où le vélo trouve sa place dans les politiques publiques locales, la pratique de ce dernier reste très inégale selon les territoires, en particulier dans les agglomérations de taille moyenne.

L'agglopôle de Sète permet d'observer les différences de traitement entre l'aménagement des infrastructures cyclables, et celui de la sécurité de l'équipement par les usagers du territoire. Sète Agglopôle Méditerranée est un établissement public de coopération intercommunale situé dans le département de l'Hérault, en région Occitanie*(figure 1)*. Il regroupe 14 communes autour de la ville-centre de Sète, bordées par la Méditerranée et l'étang de Thau *(figure 2)*.

L'EPCI de Sète a été choisie comme site d'étude, en raison de la diversité de ses communes, mêlant espaces urbains, périurbains et ruraux, permettant ainsi de mettre en perspective les conditions de la pratique du vélo selon les territoires. En outre, les zones littorales, le centre-ville dense et des typologies d'espaces résidentiels variés constituent un cadre intéressant à analyser.

En effet, la circulation à vélo est aujourd'hui un enjeu local important, notamment pour favoriser des déplacements plus durables. Ce dossier s'appuie sur les réponses à un questionnaire mené dans l'agglomération de Sète pour dresser un état des lieux de la situation. Il cherche à comprendre dans quelle mesure les aménagements et le ressenti de sécurité influencent la pratique du vélo au quotidien dans les différentes communes de ce territoire.

En quoi la qualité des infrastructures cyclables et le ressenti en matière de sécurité influencent-ils l'usage du vélo au sein de l'agglopôle de Sète ?

Ce dossier vise à fournir aux élus un état des lieux de la sécurité ressentie par les cyclistes et de la qualité des aménagements cyclables au sein de l'agglomération de Sète, à partir des réponses issues d'un questionnaire mené auprès des habitants afin d'offrir par leurs décisions, une réponse à ces disparités.

Figure 1 Carte de localisation régionale

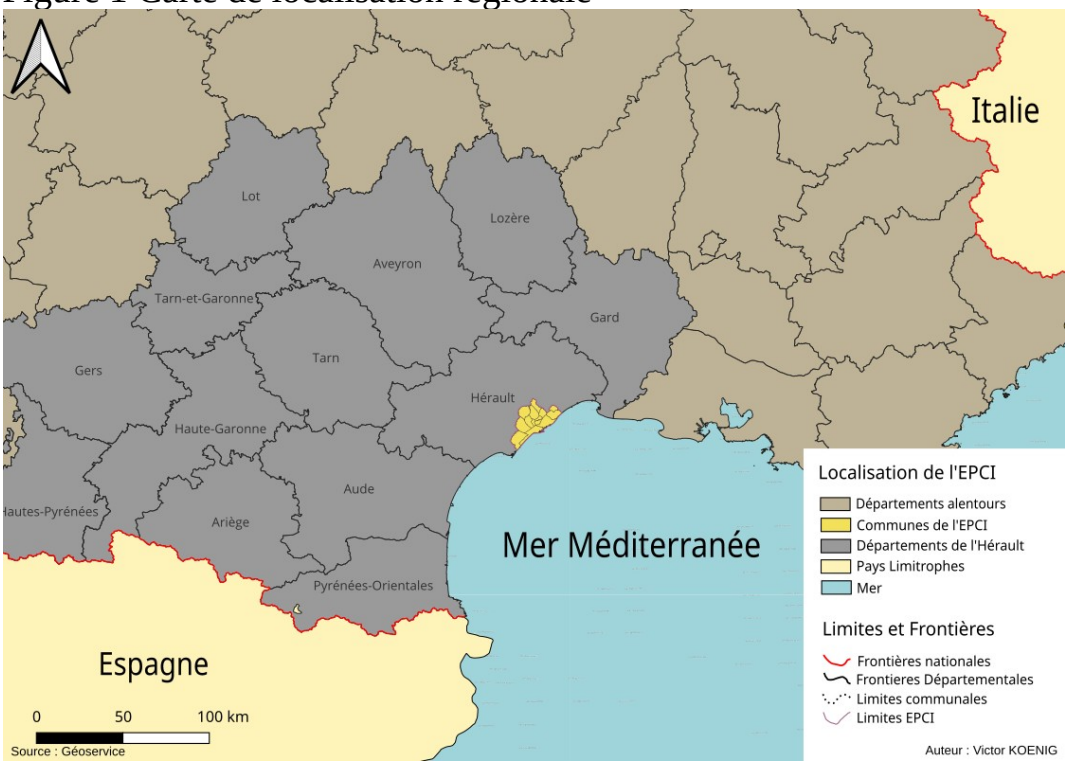

Figure 2 Carte de localisation au sein de département de l'Hérault

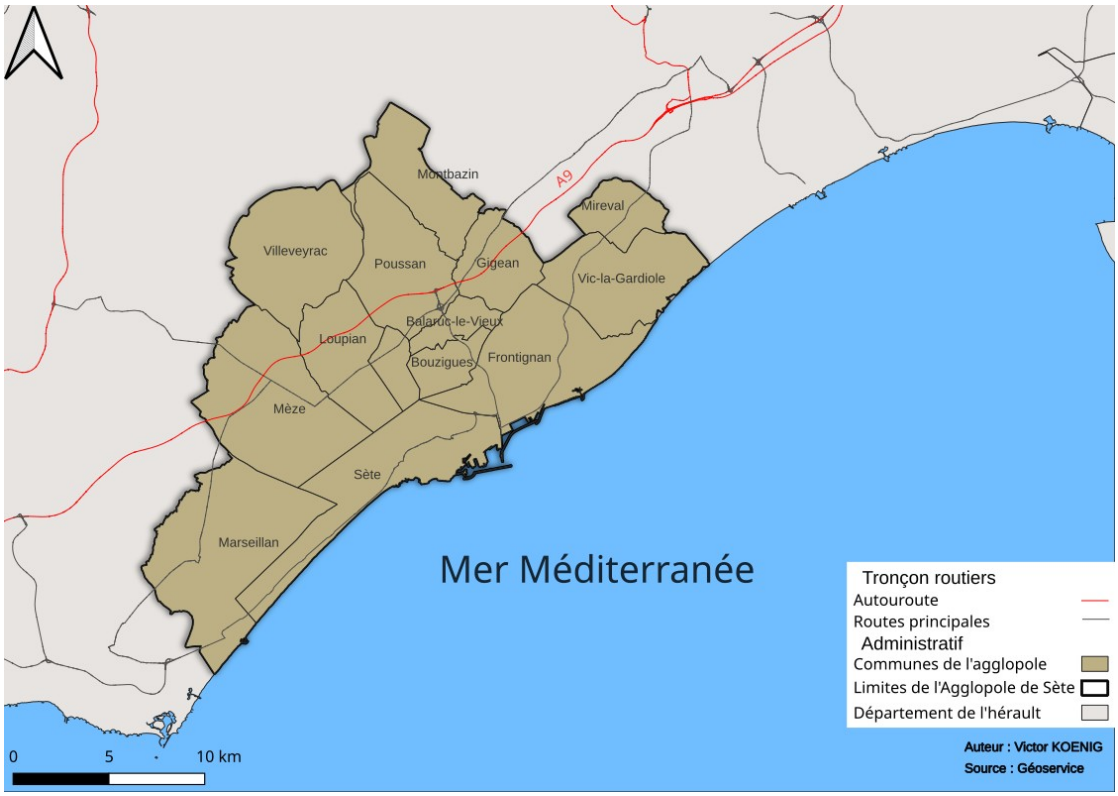

I) Les aménagements cyclables dans l’agglomération de Sète

I.1) Qualité des infrastructures selon les retours des habitants

L’analyse de l’état des aménagements cyclables révèle des disparités notables entre les communes de l’agglomération de Sète. La carte choroplèthe*(figure 3)*, élaborée à partir des résultats du sondage, met en évidence les territoires perçus comme mieux ou moins bien équipés pour la pratique du vélo. Les réponses ont été agrégées par commune afin de faire apparaître des tendances spatiales claires.

Etonnamment, les communes les plus urbaines ou centrales ne possèdent pas les infrastructures en meilleur état. En effet, on remarque que les communes avec les infrastructures perçues comme étant de meilleure qualité, sont : Bouzigues, Balaruc-le-Vieux et les-Bain ainsi que Marseillan. On remarque aussi une tendance importante pour les communes du nord de l’EPCI qui ont toutes un résultat moyen inférieur à 3 montrant un engouement potentiellement moins fort pour le cyclisme que les communes côtières voisines, bien plus prisées par les vélo, surtout au bord de la plage, avec une dynamique touristique et récréative plus importante. La lègère prédominance de communes possédant des notes inférieures à 3 se constate au moyen de l’histogramme présent. Le tableau statistique associé *(figure 4)* permet de visualiser la répartition des appréciations. Il montre 2 tendances relativement bien distinctes, avec une moitié de communes qui obtiennent des notes louables, et une autre moitié qui semble beaucoup plus délaisser ses infrastructures cyclables.

Figure 3 : Carte choroplèthe des résultats moyens par communes sur l'entretien des infrastructures cyclables

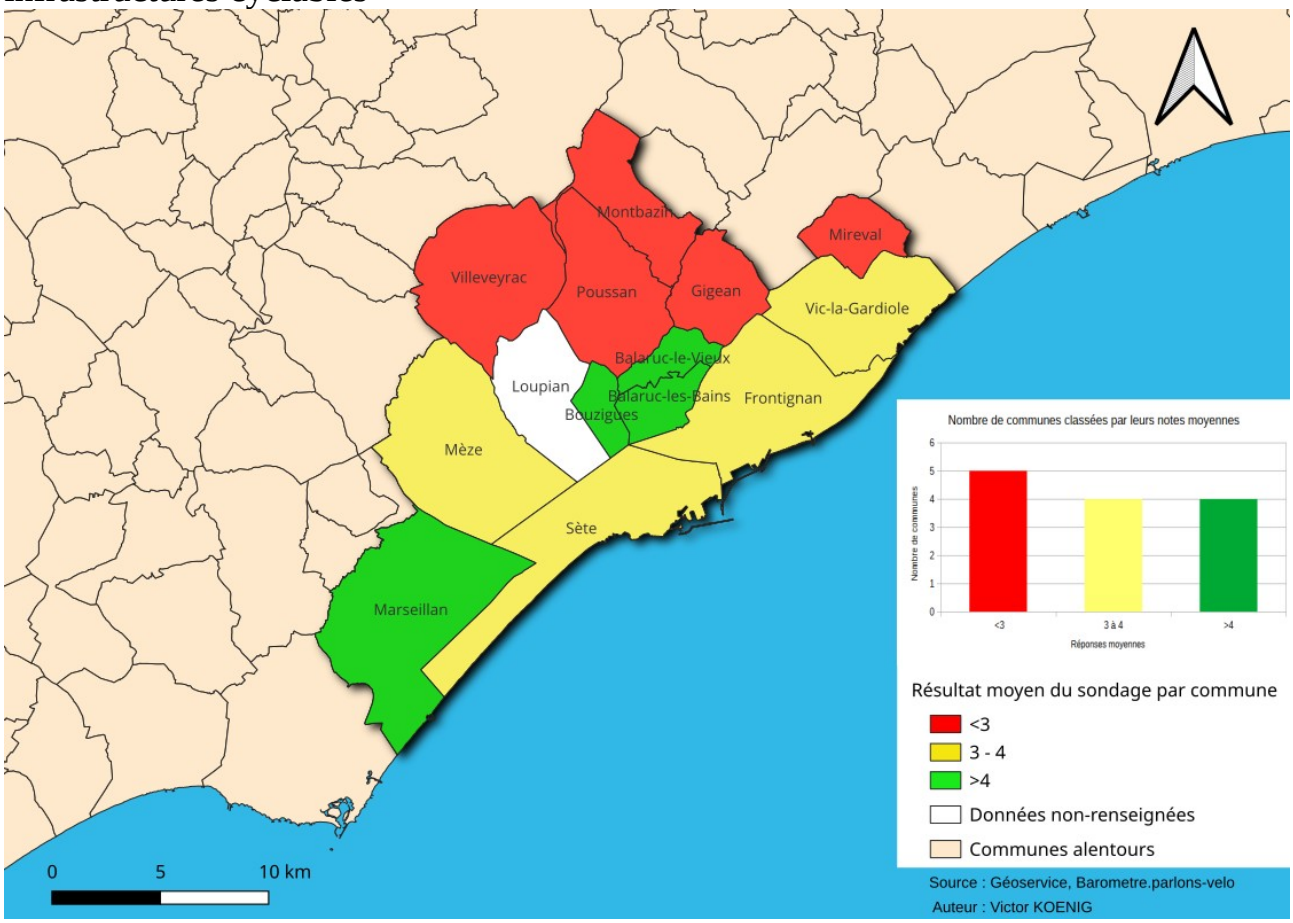

Figure 4

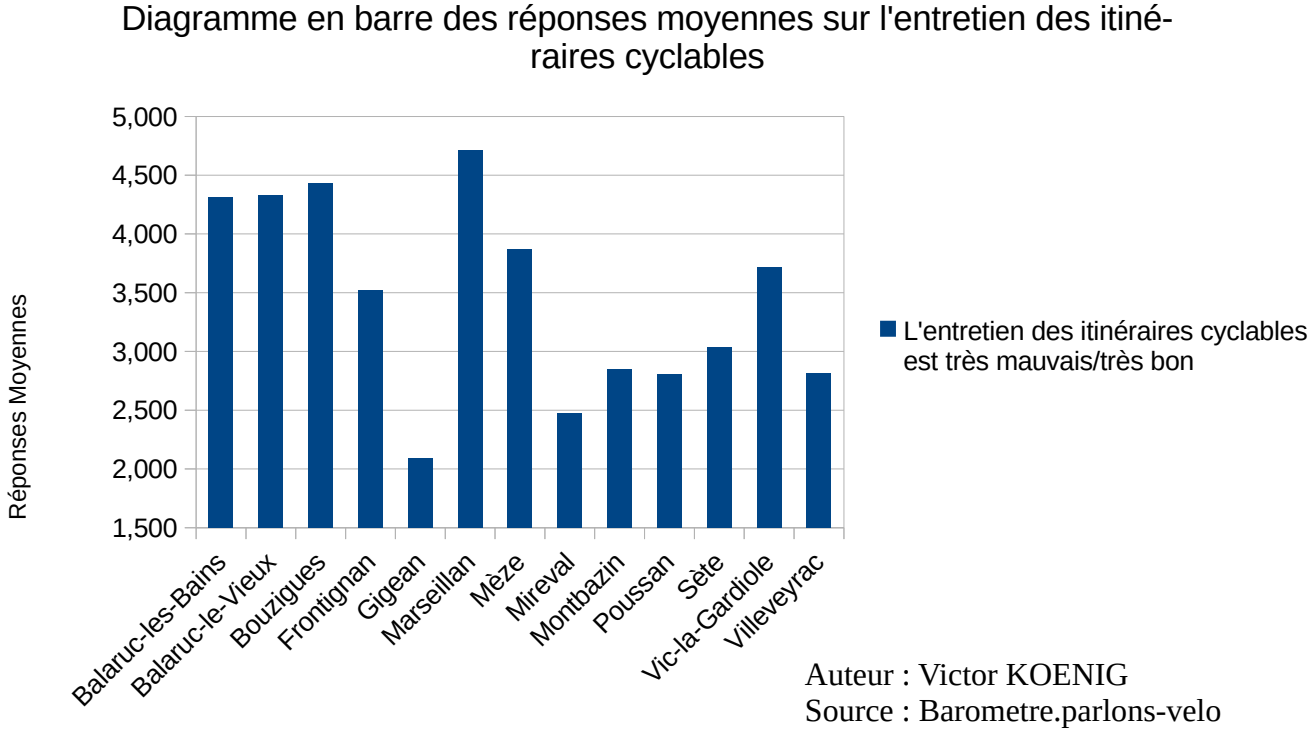

Auteur : Victor KOENIG
Source : Barometre.parlons-velo

I.2) Perception des efforts communaux en faveur de vélo

Afin de confirmer ces résultats sur l'état des infrastructures cyclables dans les communes l'analyse des réponses sur les efforts des communes en faveur du vélo ressenti par les cyclistes semble plus que pertinent.
Le diagramme en bâtons ci-dessous *(figure 5)* illustre les réponses moyennes à la question du ressenti sur les efforts faits en faveur du vélo dans chaque commune. On y observe de fortes disparités à l'instar de du diagramme précédent. Marseillan se distingue très nettement, avec une moyenne qui dépasse les 5, loin devant ses communes voisines, indiquant une perception très positive des aménagements ou des actions entreprises. À l'inverse, des communes comme Gigean, Mireval ou Montbazin présentent des scores inférieurs à 2, traduisant un sentiment d'abandon ou d'inaction perçu par les répondants. Certaines communes comme Frontignan, Mèze ou Bouzigues présentent des résultats plus intermédiaires, suggérant des efforts jugés partiels ou inégalement répartis. Les données traitées ici sont donc en adéquation partielle avec les données précédentes, avec certaines communes qui auront d'encore meilleures notes ou d'encore pires notes, et d'autres communes, plus moyennes, avec des notes orbitant autour des 3. Il est ainsi légitime de se demander pour qu'elles raison certaines communes qui obtenaient des notes supérieures à 4 lorsqu'il est question de l'entretient des itinéraires cyclables, et des notes parfois inférieures à 3,5 en ce qui concerne les effort des communes. Une hypothèse à explorer serait sûrement que les villes dans cette situation possèdent des infrastructures vieillissantes, bien qu'entretenues donnant ainsi un ressenti pour les usager de manque d'effort, car peu de changement sont visibles malgré des pistes propres.

Figure 5

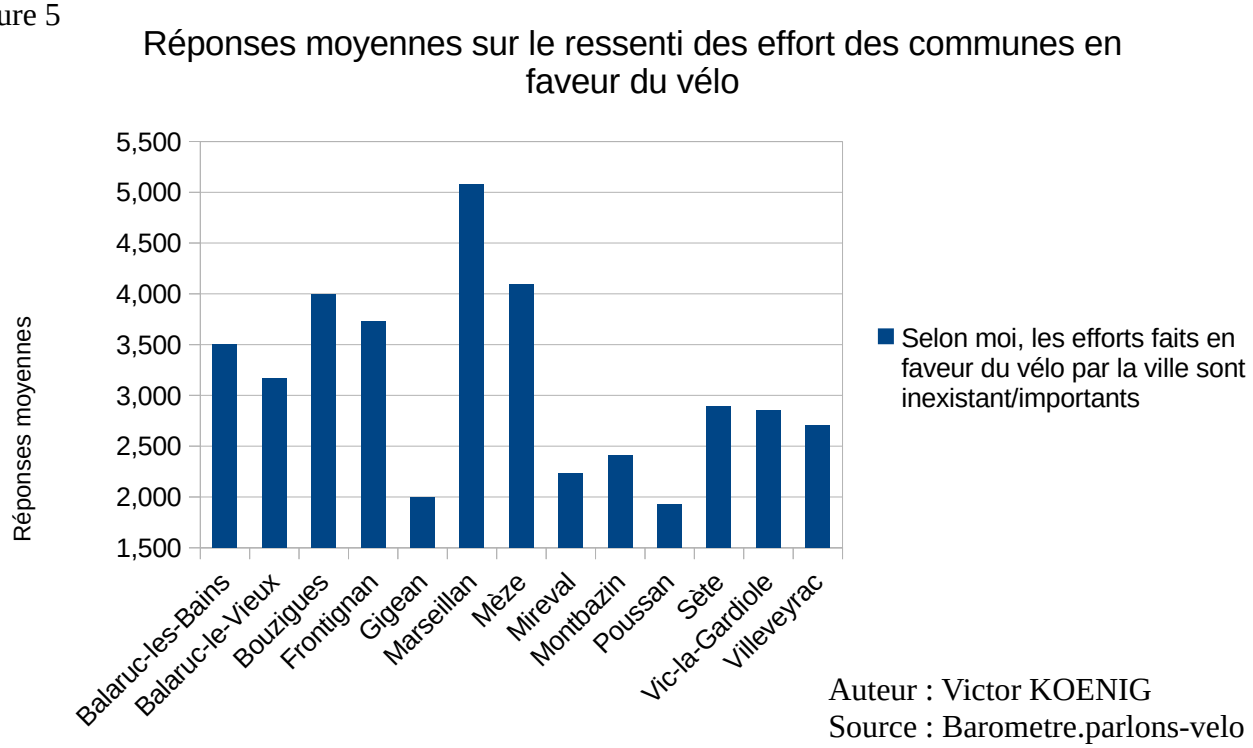

Auteur : Victor KOENIG
Source : Barometre.parlons-velo

II) La sécurité des cyclistes au quotidien

II.1) Ressenti global en matière de sécurité à vélo

Il convient à présent d'interroger la perception des cyclistes en matière de sécurité après avoir exposé l'état des infrastructures cyclables. En effet, la qualité des aménagements peut avoir un impact considérable sur la perception que se font les usagers de leur sécurité au quotidien. De ce fait, l'étape suivante du travail consiste à se demander si l'état des infrastructures contribue, ou non, au ressenti de sécurité des cyclistes et si une relation peut être établie entre ces deux dimensions.

L'étude de la carte du ressenti de sécurité *(figure 6)* couplé au digramme traitant de la même variable *(figure 7)* en barre révèle qu'un certain nombre de communes se répartissent harmonieusement entre les deux extrêmes. Elles se placent entre les notes de 3 et 4, créant une majorité dans le registre d'une sécurité modérée. Deux communes sont, par contre, en bonne place dans le registre des positives : Marseillan et Mèze se positionnent ainsi au-dessus de 4. Ce constat s'aligne avec l'orientation des résultats précédents esquissant une qualité d'infrastructures cyclables relativement établie, voire bien développée, ce qui pourrait être le signe d'une certaine corrélation entre la qualité des aménagements et la sécurité ressentie. L'histogramme présent permet néanmoins de constater la baisse du nombre de communes possédant plus de 4 montrant une baisse de l'estime de sécurité à l'égard de l'entretien.

À l'inverse, pour Sète, la notation est inférieure à 2, révélant un sentiment d'insécurité très prononcé, qui rejoint les précédentes analyses mettant en évidence un déficit ou une vétusté du réseau. Une nuance doit quand même être précisée concernant la ville de Sète. En effet cette dernière est bien plus importante et dense que ses communes voisines rendant la ville plus enclin à recevoir un nombre bien plus conséquent de véhicule motorisé. Cela rend ainsi, si pistes cyclables manquent, le trajet en vélo bien plus dangereux.
Quant au communes du nord de l'agglopôle que Poussan, Gigean ou Villeveyrac, également notées sous 3, le constat est similaire que pour les question précedemment analysées.

En synthèse, même si la concordance entre qualité des infrastructures et sécurité perçue n'est pas uniforme, elle est observable dans plusieurs situations. Ce qui souligne à la fois la nécessité d'aménagements cyclables adaptés mais également d'actions associées, en faveur des cyclistes, telles que la mise à disposition d'éléments d'information afin de renforcer confort et confiance

Figure 6 Carte choroplèthe des résultats moyens par communes sur la sécurité ressentie par les cyclistes lors de trajet à vélo

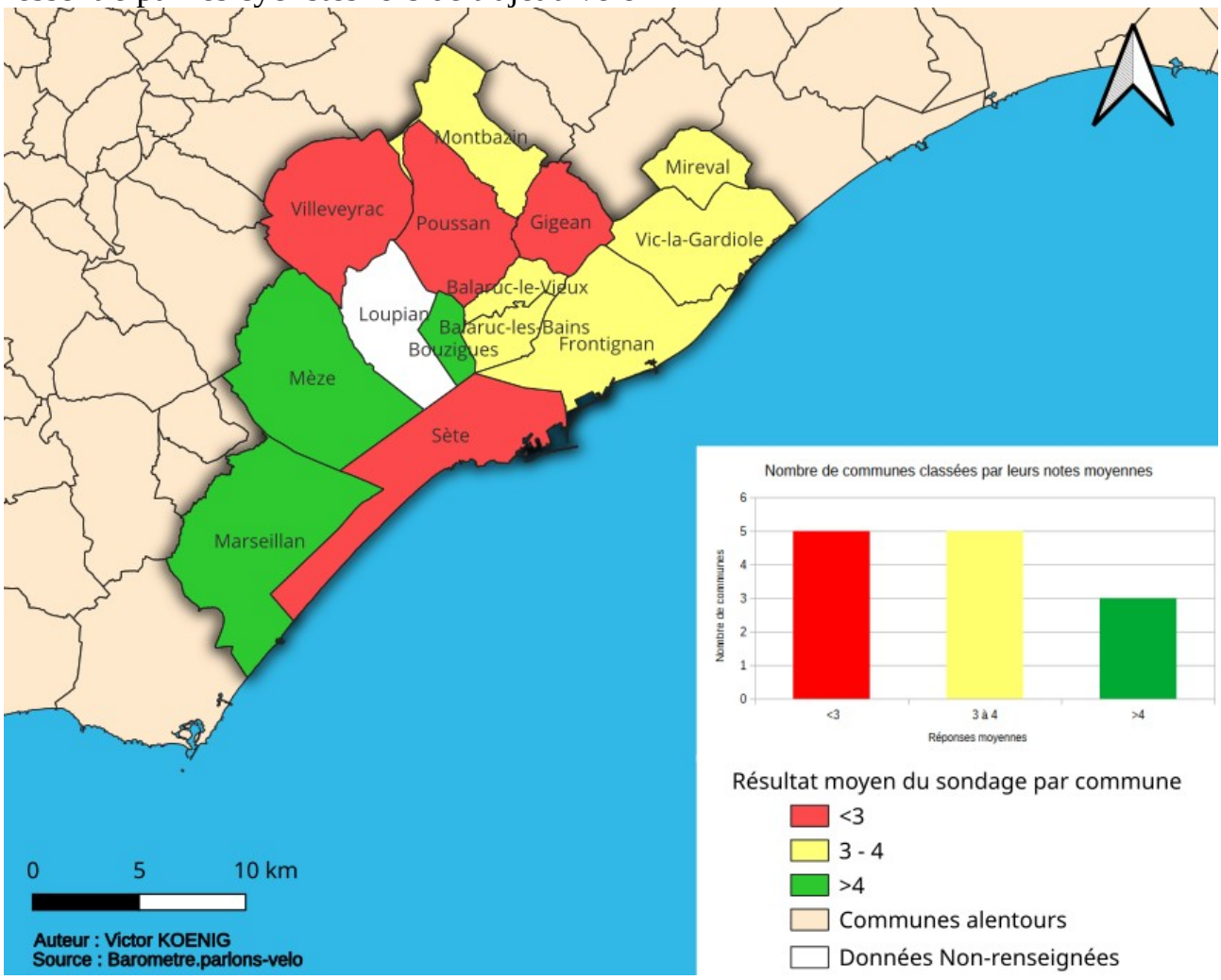

Figure 7

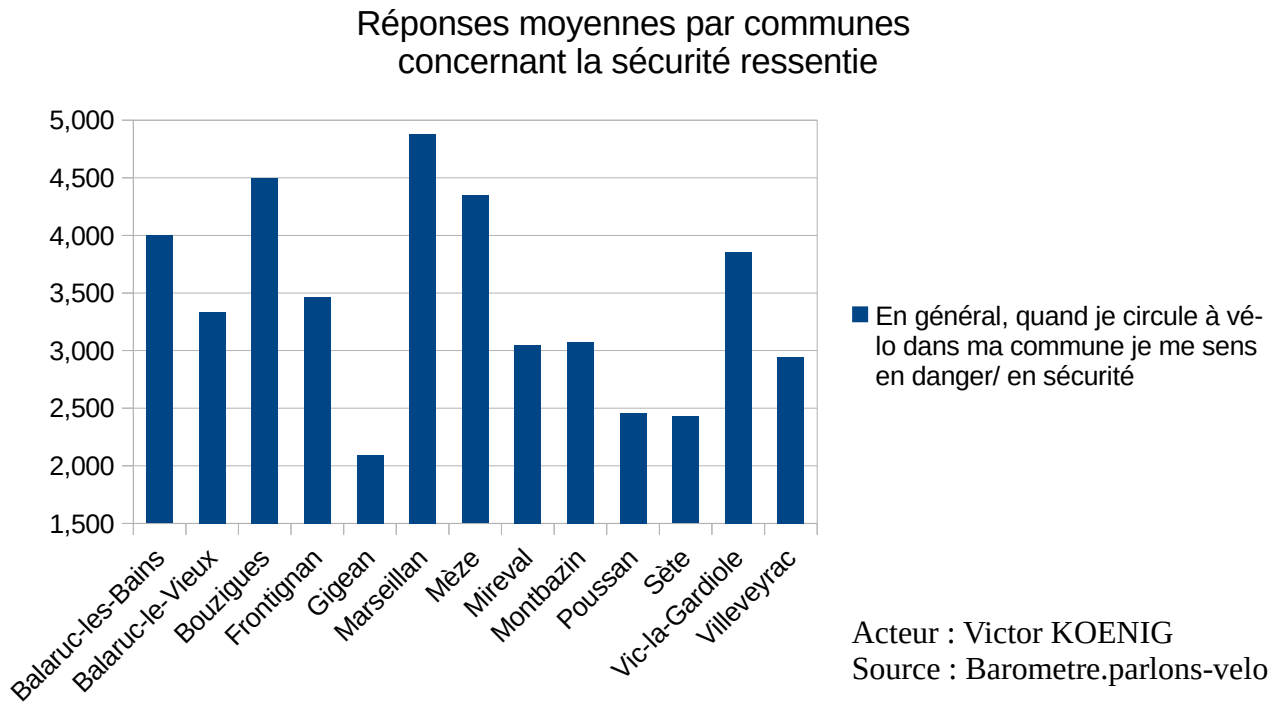

II.2) Lecture croisée entre qualité des aménagements et sécurité perçue

Après avoir examiné séparément la qualité des infrastructures cyclables et le ressenti de sécurité des usagers, il paraît essentiel de croiser ces deux dimensions. Cette synthèse permet de dégager des typologies territoriales et de vérifier s'il existe une corrélation entre l'état perçu des aménagements cyclables et le sentiment de sécurité. Pour ce faire, une carte typologique a été produite, accompagnée d'un diagramme de dispersion, afin d'apporter une lecture plus fine des relations entre ces deux variables. Ce qui a été tout d'abord l'étude séparée de l'entretien des infrastructures et du sentiment de sécurité des cyclistes prend son sens dans une lecture croisée.

La carte typologique *(figure 8)* ci-dessous fait correspondre les communes selon ces deux variables, le diagramme de répartition quant à lui, révèle la corrélativité lors de des deux variables utilisées. Les communes telles que Marseillan, Mèze ou Frontignan, ici en vert, sont ainsi bien entretenues et bien perçues en matière de sécurité. Tout à fait à l'opposé de Villeveyrac, Gigean ou Poussan présenté ici en rouge, qui sont clairement dans une position difficile sur les deux champs. Les cas intermédiaires, comme Sète en orange, montrent un entretien jugé acceptable, mais un sentiment d'insécurité pour autant présent, lié à un contexte plus dense comme déjà émis précédemment. Le diagramme de points met encore plus en avant ce sens de lecture : l'on perçoit une corrélation relativement linéaire entre état des infrastructures et sentiment de sécurité, renvoyant donc à l'impact direct de la question de la qualité de l'usage cyclable. Une corrélation de Pearson a été effectuée afin d'appuyer sur l'hypothèse. Le résultat de ce calcul a mené au résultat de 0,87 rendant une corrélation linéaire plus que satisfaisante. En effet, une corrélation linéaire forte et positive est perçue entre les deux variables étudiées car, dans les faits, l'augmentation de l'une va de pair avec l'augmentation de l'autre.

Figure 8 : Carte de typologie de croisement entre la variable de sécurité et d'entretien des infrastructures

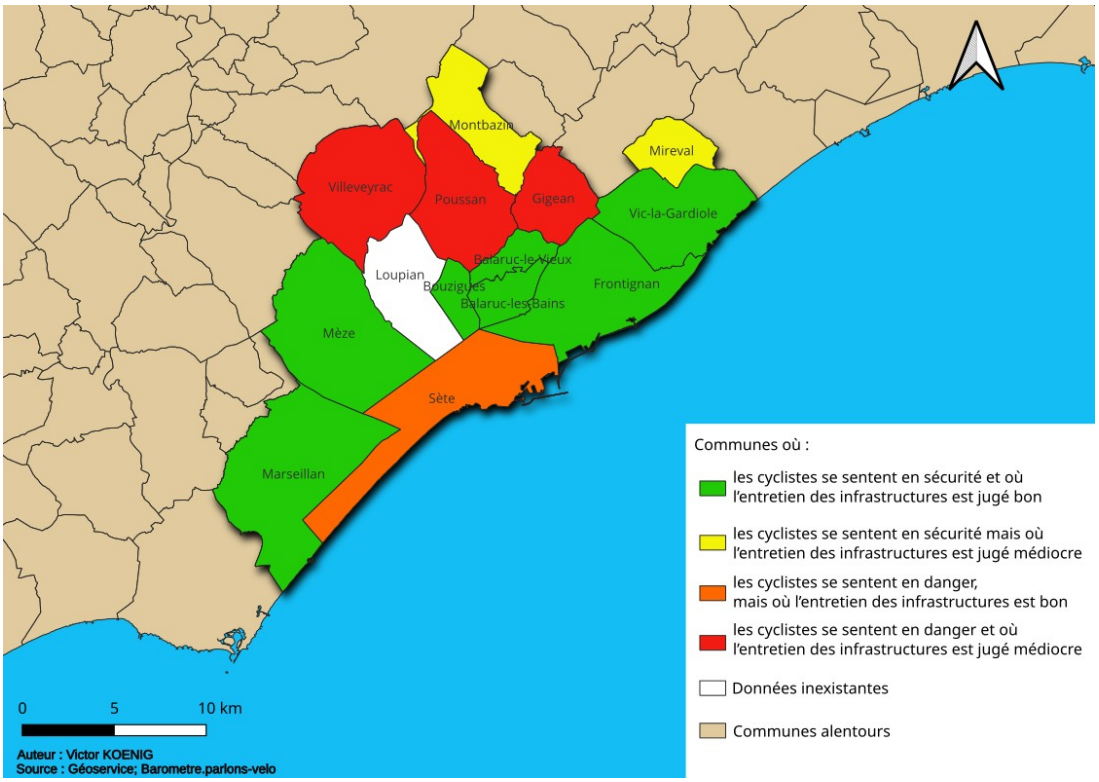

Figure 9

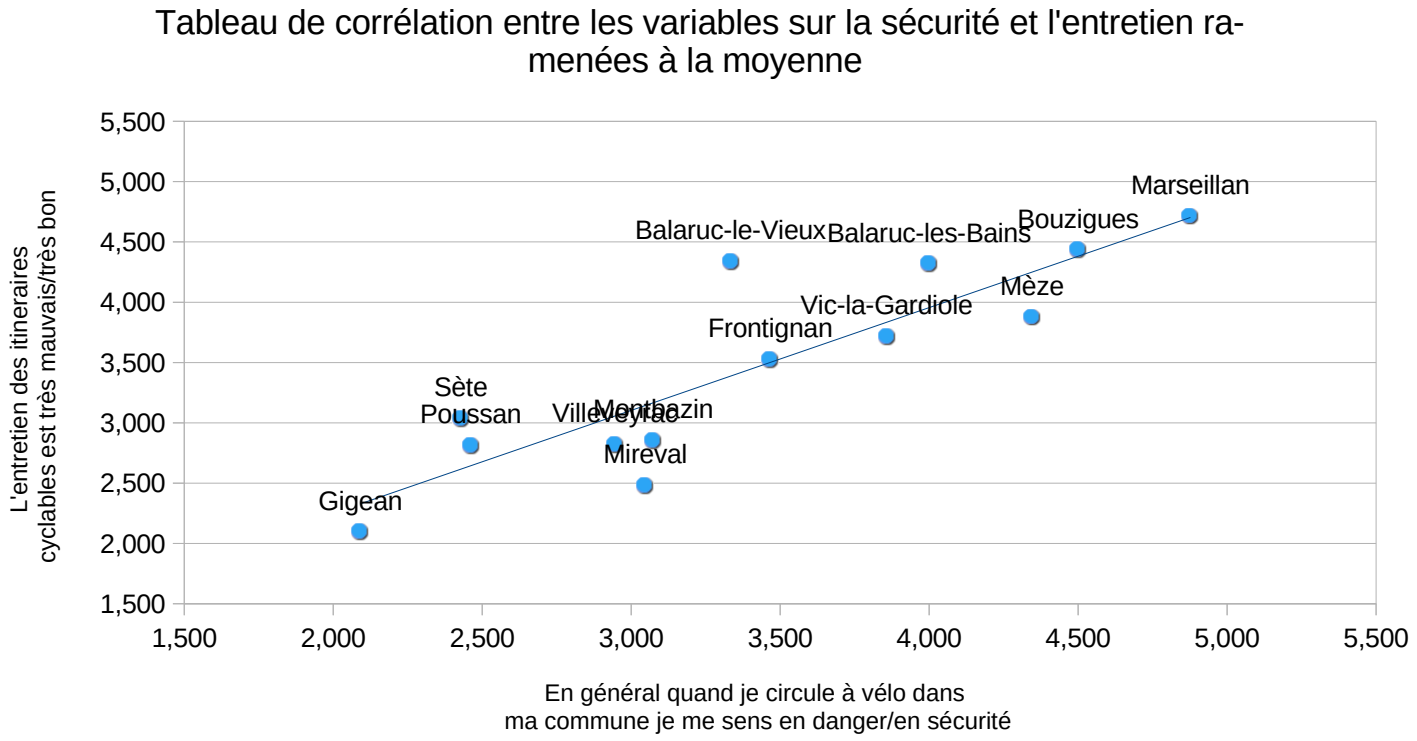

Auteur : Victor KOENIG
Source : Barometre.parlons-velo

III) La fiabilité des données peut-elle être remise en cause par une insuffisance de réponses ?

III.1) Taux de réponse relatif aux habitant très disproportionné

Bien que les résultats du sondage mettent en lumière un certain malaise concernant la sécurité des cyclistes et l'état des infrastructures sur l'agglomération de Sète, leur fiabilité doit être relativisée et remise en question. En effet, lors d'une analyse plus fine des réponses, les résultats révèlent de fortes disparités territoriales. La carte choroplèthe associée *(figure 10)* montre que certaines communes, notamment Marseillan au sud-ouest, ainsi que Villeveyrac et Mireval au nord, concentrent une part 'importante' des réponses c'est à dire jusqu'à 2 %, tandis que d'autres, parfois très peuplées, sont presque absentes de l'échantillon comme Sète ou Frontignan. Cette analyse permet d'une part de confirmer encore plus la situation exemplaire de Marseillan, puisque la commune concentre les meilleures notes ainsi que le meilleur rapport répondant/habitant de l'agglopôle.
L'inégale répartition des réponses pose alors question : les résultats livrés sont-ils à classer dans la réalité mis en avant par le sondage ou faut-il considérer, en raison de ces réalisations disparates, le biais de participation, en dépréciant certains résultats, qu'ils soient satisfaisants ou non. La réponse la plus habile à cette question est sûrement celle de l'objectivité ainsi que de l'esprit critique. En effet le résultat de ce sondage montre des problèmes évident mais peut être parfois démesuré en comparaison avec la réalité. Ces résultat restent donc pertinent malgré une nuance évidente à mettre en place.

Figure 10 : Carte choroplèthe du taux de réponse relatives à la population totale par commune

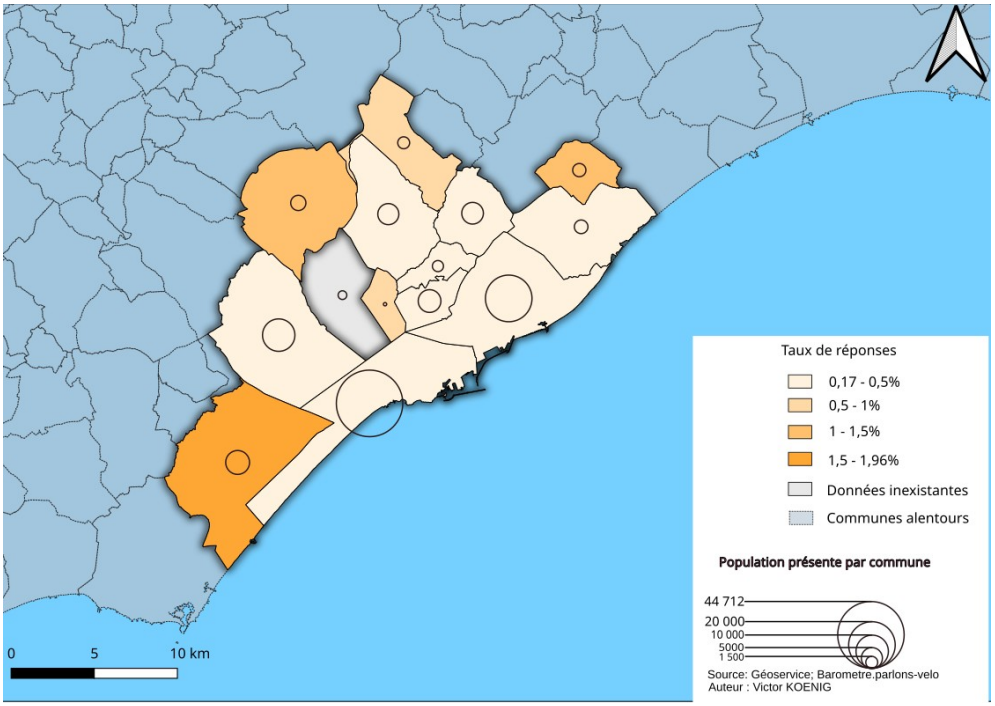

III.2) En inadéquation avec le recensement total des points

De plus, la carte choroplèthe qui suis *(figure 11)* montre un angle différent de la situation des communes. Cette dernière montre un aspect global de la qualité du déplacement à vélo dans l'agglopôle par le biais de la présence : de points noirs qui par représentation géographique montrent les points à améliorer en priorité selon les répondants du baromètre, ainsi que de points blancs qui décrivent quant à eux les améliorations perçues depuis 2 ans par les répondants. Le constat diffère alors complètement de l'idée émise sur les communes 'bonnes élèves' et celles avec des notes plus médiocres. En effet la carte montre que pratiquement toutes les communes de l'agglopôle possèdent une dominance de point noirs, c'est à dire une présence supérieur à 50 % par rapport aux points blanc, quelque soit le nombre de points recensés. Marseillan qui brillait jusque là fait alors pâle figure avec une présence dominante de points noirs. D'autres communes comme Gigean ou Mireval confirment au contraire les perceptions plus critiques exprimées dans le sondage, avec une proportion importante de points noirs recensés. La carte souligne donc une forme de dissonance entre l'impression générale des usagers et la réalité spatiale du constat. Ainsi même dans les communes jugées globalement favorables au vélo, les tensions demeurent localement et viennent concentrer les insatisfactions sur des secteurs stratégiques du réseau cyclable. Le croisement des deux lectures, synthétique par le biais du diagramme et territorialisée via la carte, permet en somme d'enrichir l'analyse et de renforcer l'idée que des efforts ciblés sont encore nécessaires, y compris sur des territoires jugés comme attentifs au vélo.

Figure 11 : Carte choroplèthe de la prévalance des points noirs dans les territoirs communaux

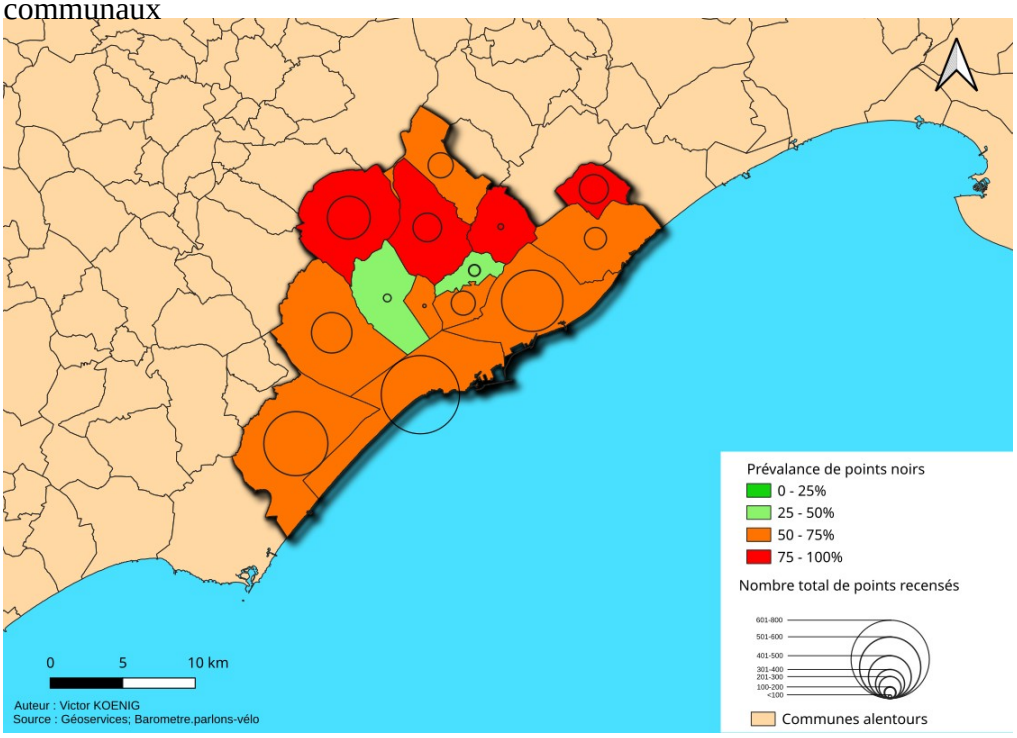

Conclusion

À l’issue de cette analyse, la qualité de l’infrastructure cyclable et le ressenti éprouvé en matière de sécurité demeurent des éléments qui font la différence en matière de l’usage du vélo au sein de l’agglopôle de Sète. Pour certaines communes, les retours des usagers peuvent être favorables, sans que l’on puisse pour autant occulter les points noirs identifiés sur le territoire, y compris sur le foncier a priori favorable. L’écart entre le ressenti général des habitants et la réalité territoriale des dysfonctionnements témoigne de la nécessité de disposer de politiques d’aménagement ciblées et enfin cohérentes. L’usage du vélo n’est pas seulement un enjeu d’aménagement ; il envoie des signaux plus globalement liés à l’accessibilité, la sécurité, la lisibilité des itinéraires et la confiance des usagers. Cependant, l’évaluation de ces données doit se faire avec une certaine distance critique. Le faible taux de participation au baromètre vélo dans plusieurs communes appelle à la prudence dans l’interprétation des résultats. Les conclusions tirées ici, bien qu’indicatives, reposent en effet sur des données partielles. On ne peut les considérer comme fidèles à l’ensemble des perceptions des habitants. D’où l’importance d’être méthodiquement objectif et critique dans l’évaluation du territoire pour éviter les généralisations hâtives et préciser les réels besoins du territoire. Ainsi, pour développer la pratique cyclable de façon durable, l’agglopôle devra conjuguer amélioration du réseau concret et sentiment de sécurité d’un côté, outils de mesure plus représentatifs et inclusifs de l’autre.

Sources

https://www.insee.fr/fr/metadonnees/geographie/intercommunalite/200066355-sete-agglopole-mediterranee

https://geoservices.ign.fr/catalogue

https://barometre.parlons-velo.fr/2021/